Présentation de l'outil de production et de gestion des métadonnées MDweb

Rabat – Mars 2004

Objectifs

✍ Recenser et cataloguer les données environnementales

✍ Stocker et gérer les métadonnées à travers une base de données relationnelle

✍ Assurer la consultation du catalogue… et plus tard l'accès à la donnée

✍ Permettre l'exportation/importation des métadonnées au format d'échange XML

Spécifications et fonctionalités de MDweb

Spécifications techniques

✍ Basé sur le logiciel libre : serveur Apache, langage PHP, SGBD gratuits

✍ Multi-systèmes : Unix ou Windows

✍ Multi-SGBD : Postgres, MySQL, (ORACLE?)

✍ Multi-langues : anglais, français, autres langues paramétrables

✍ Multi-normes : ISO par défaut, possibilité d'ajouter d'autres normes de métadonnées

Architecture de l'outil

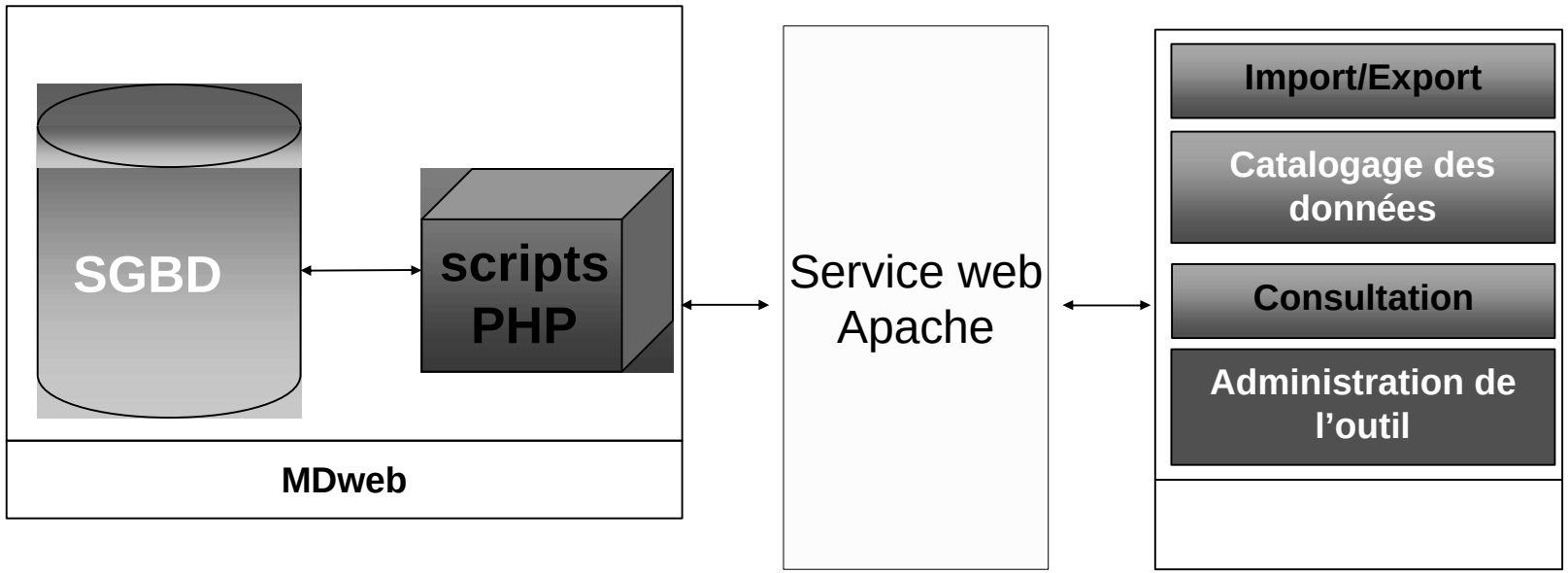

Structuration des métadonnées

✍ Choix d'une norme de métadonnées : ISO 19115

✍ Personnalisation pour ROSELT à travers la description de formulaires selon la ressource à référencer

✍ Saisie des fiches de métadonnées selon la structure par les formulaires

Structure générale de la base

Fiches de métadonnées

Description des formulaires

Dictionnaire de(s) (la) norme(s)

Fonctionnalités

- Accès sécurisé par mot de passe
- Personnalisation : choix de la couleur et de la langue des interfaces pour chaque utilisateur
- Saisie et mise à jour des fiches de métadonnées
- Consultation des fiches

Fonctionnalités

✍ Administrer l'outil : gestion des utilisateurs, des langues, des formulaires de saisie

✍ Import/export : interaction avec les métadonnées issues d'autres sources (SIEL), envoi vers l'outil de gestion des métadonnées régional

Fonctionnalités à venir

✍ recherche par localisation géographique à partir d'un outil cartographique permettant de spécifier la localisation

✍ Module de requêtes distribuées permettant l'accès à tous les catalogues

✍ attachement de la donnée à une fiche du catalogue

✍ modules de génération des métadonnées et export vers MDweb dans les outils de production des données (ArcGis, Ms-Office, etc.)

Intégration de MDweb au sein de l’institution nationale et dans le réseau d’observatoires ROSELT

Intégration de l'outil

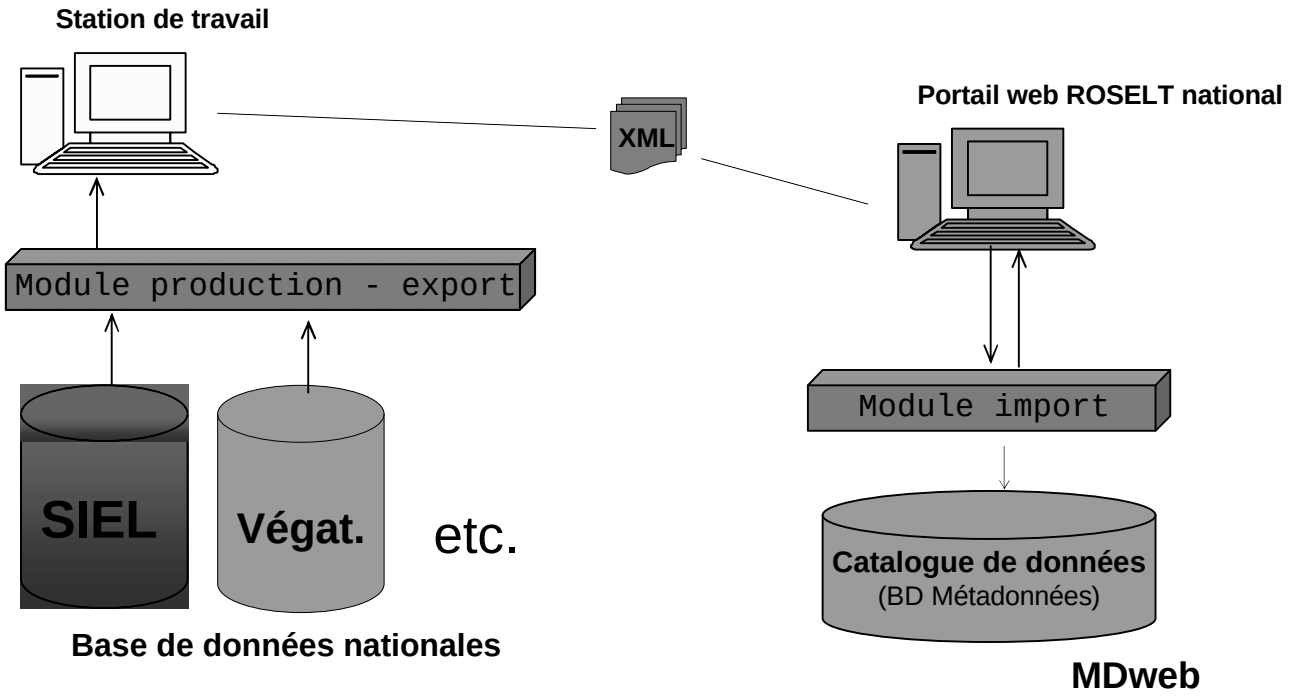

Déploiement de l’outil

✍ Outil local : pour le recensement et la consultation du catalogue de données des observatoires du pays

Connexion à un catalogue national

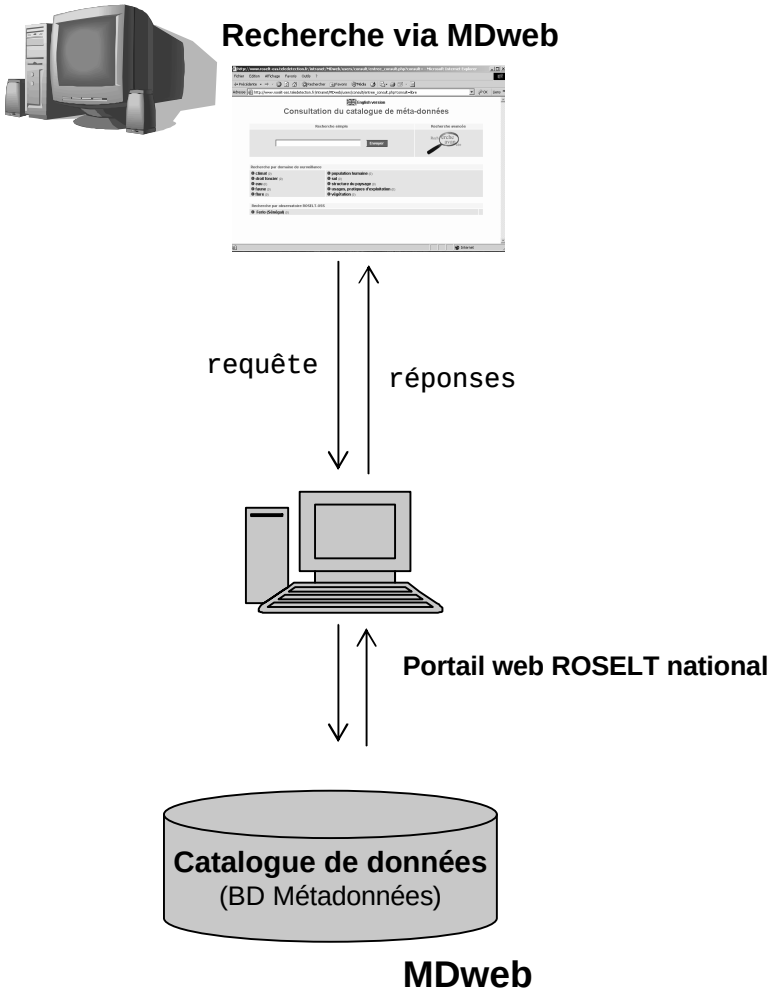

Déploiement de l’outil

✍ Outil régional : pour la consultation du catalogue régional ROSELT de l’ensemble des observatoires et la gestion des normes

Connexion au catalogue régional

requête

réponses

Portail web ROSELT régional

Recherche via MDweb

Requêtes multiples

Résultats interrogations multiples

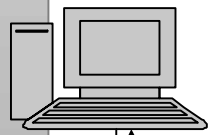

Portail web ROSELT national

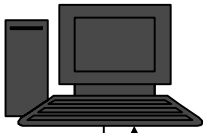

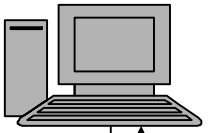

Protocole d'échange

Protocole d'échange

Protocole d'échange

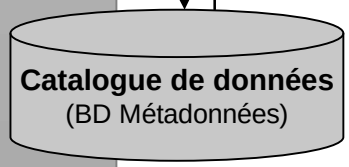

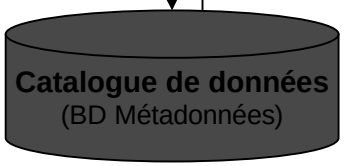

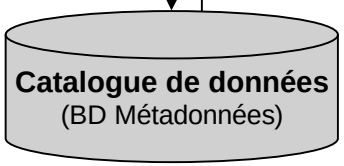

MDweb

MDweb

MDweb

Fonctionnalités et rôles
Pour l'utilisation et la gestion des catalogues de données ROSELT

Fonctionnalités / Rôles

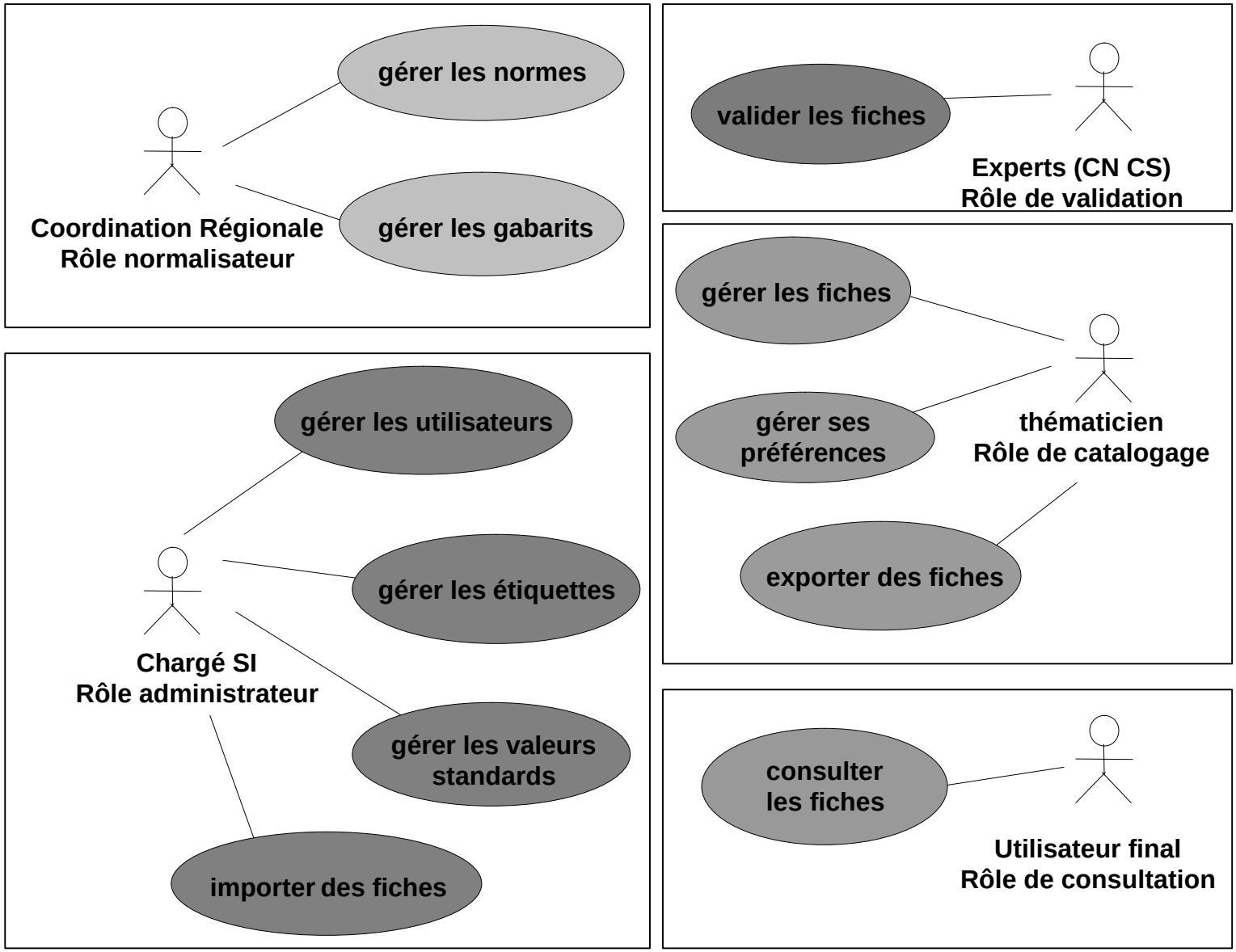

Recensement et catalogage des données de votre observatoire

Recensement & catalogage

✍ Constituer un catalogue de référence des données historiques, actuelles et futures

✍ Pouvoir connaître facilement via un index ou un formulaire de recherche l'existence et la pertinence de jeux de données

✍ Dans un futur proche, Accéder aux données via le catalogue

Notion de ressource

✍ Ressource analogique : Une carte papier, un rapport, un ouvrage, une image aérienne sur support argentique, etc.

→ Cas où la ressource et sa description se rapporte à un document

✍ Ressource numérique : base de données relationnelle, base de données géographique, carte numérique,etc.

→ Que décrit–on ? : l'ensemble, les composants, les caractéristiques des composants

Exemple d'une ressource numérique : Carte d'occupation des terres

Collection de données

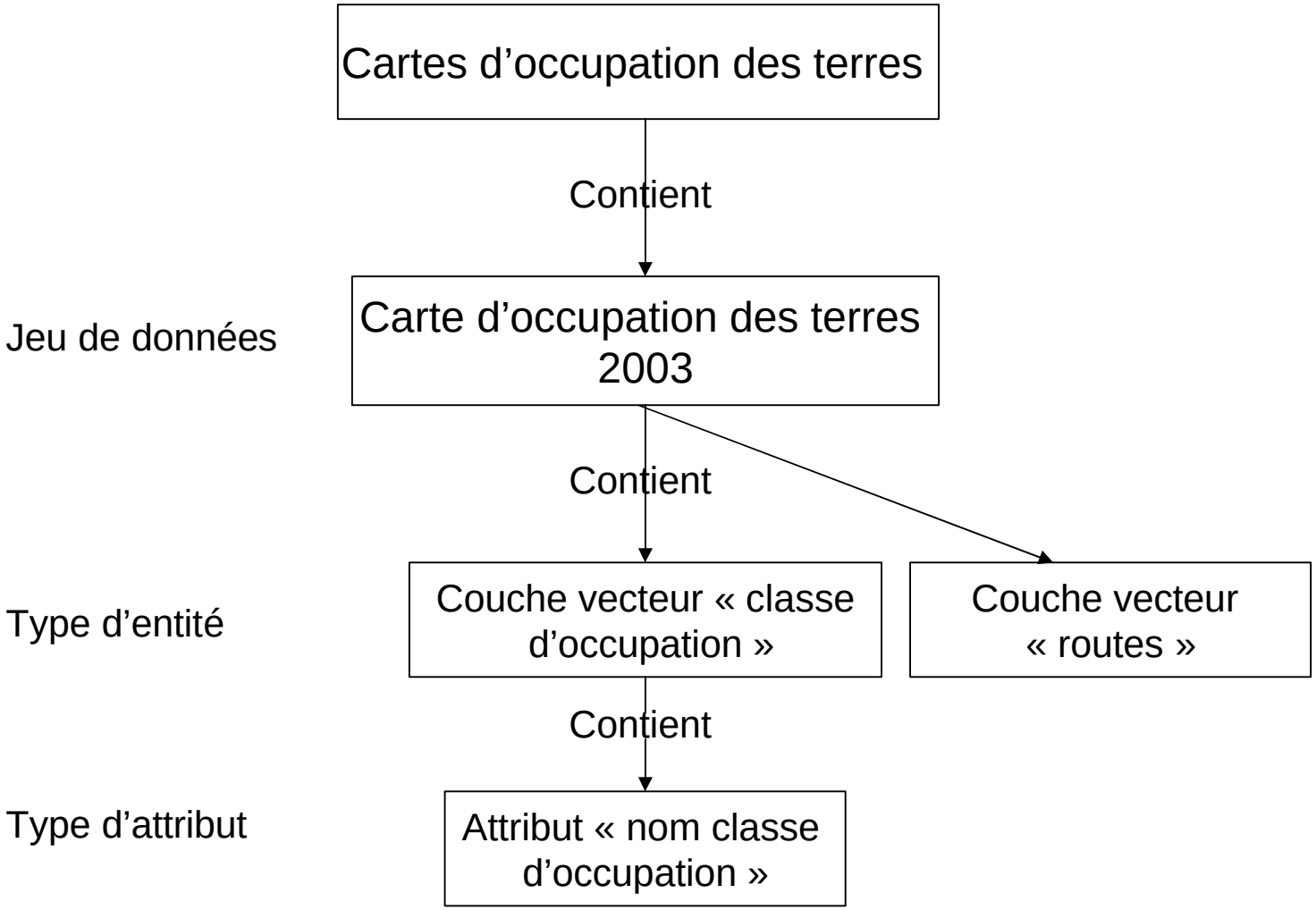

Exemple d'une ressource numérique : Carte d'occupation des terres

Collection de données

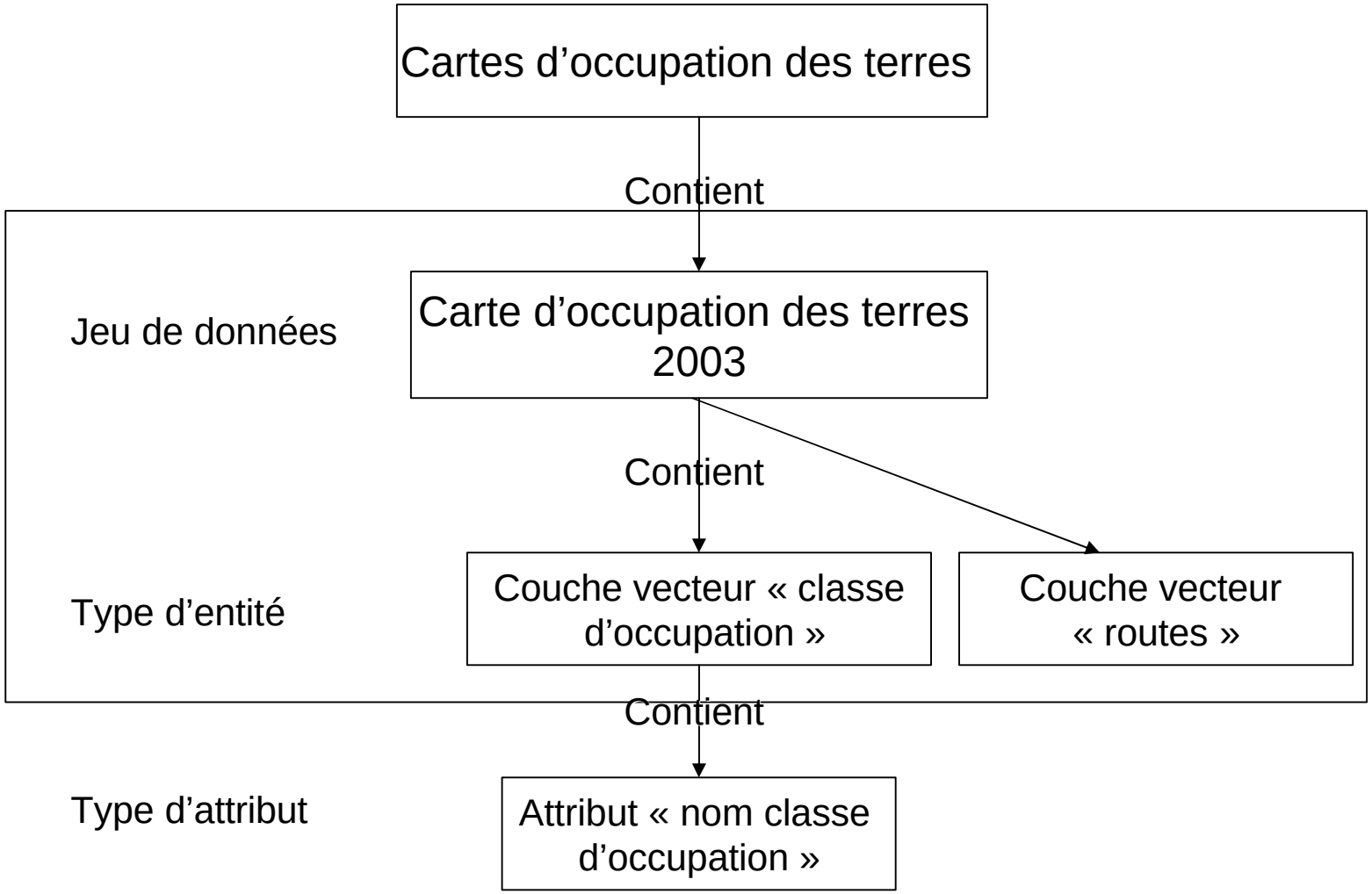

Typologie des ressources dans ROSELT

Mesures de terrain

- ??Inventaire de végétation
- ??Inventaire des habitats, de la flore et de sa diversité
- ??Inventaire des habitats, de la faune et de sa diversité
- ??Campagne d'enquête socio-économie
- ??Campagne de relevés pédologiques
- ??Campagne de relevés bioclimatiques

Infos géoréférencées

- ??Carte papier
- ??Carte numérique
- ??Couche d'information vecteur
- ??Couche d'information raster
- ??Image satellitale brute ou pré-traitée
- ??Image aérienne papier
- ??Image aérienne numérique
- ??Base de données géographique

Infos Non géos

- ??Base de données non géographique
- ??Document papier
- ??Document numérique
- ??Tableau papier
- ??Tableau numérique

Formulaires de saisie disponibles

Mesures de terrain

- Inventaire de végétation
- Inventaire des habitats, de la flore et de sa diversité
- Inventaire des habitats, de la faune et de sa diversité
- Campagne d'enquête socio-économie
- Campagne de relevés pédologiques
- Campagne de relevés bioclimatiques

Infos géoréférencées

- Carte papier
- Carte numérique
- Couche d'information vecteur
- Couche d'information raster
- Image satellitale brute ou pré-traitée
- Image aérienne papier
- Image aérienne numérique
- Base de données géographique

Infos Non géos

- Base de données non géographique
- Document papier
- Document numérique
- Tableau papier
- Tableau numérique

Elaboration des fiches du catalogue

Proposition de formulaire papier pour préparer l'insertion dans MDweb

- Rubriques et champs obligatoires

Ils proposent un ensemble d'éléments indispensables au catalogage qui seront communs à toutes les ressources et tous les observatoires ROSELT

- Rubriques et champs facultatifs

Permettent de répondre à une description plus précise de la ressource et assure une souplesse dans la description

Propositions pour la structuration et la gestion du catalogue de données ROSELT Maroc

Structuration du catalogue au Maroc

- Plusieurs collections ou base de données identifiées dans le cadre de la surveillance :
- Carte et images satellitales de référence
- Base de données géomorphologique, pédologique, érosion
- Base de données Faune
- Base de données Végétation

Structuration du catalogue au Maroc

- Base de données socio-économique
- Base de données SIEL

Gestion du catalogue au Maroc

- Rôle du chargé SI :

  Gestion de l'outil : maintenance , mis à jour, gestion des utilisateurs, cohérence

  Formation des thématiciens à son utilisation

- Rôle des thématiciens : référencer et documenter leur données dans le catalogue

  les producteurs de la donnée sont les mieux placés pour référencer et documenter leurs données

- Rôle des Coordinateur d'observatoire, scientifique ou national

  Valider le contenu du catalogue (pertinence, cohérence du contenu du catalogue)